3 - מאושרת

תשריט מס' ת/500

מרחב תכנון מקומי תל-אביב - יפו
תשריט לתכנית מס' 1482
שנוי מס' 2 לשנת 1971 של 253

תכנית מפורטת מס'

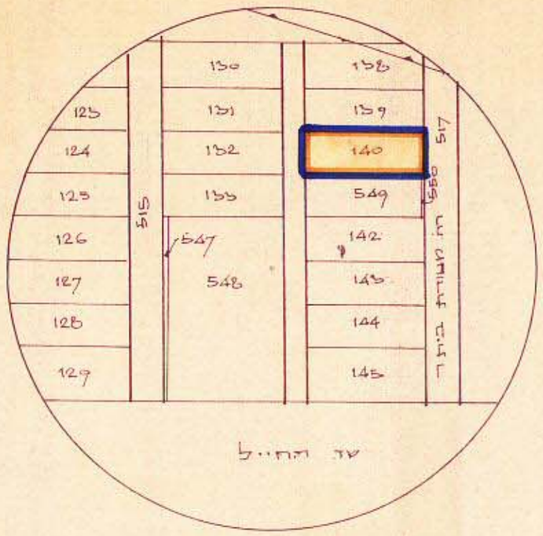

תרשים הסביבה

1:1250 ק.מ.

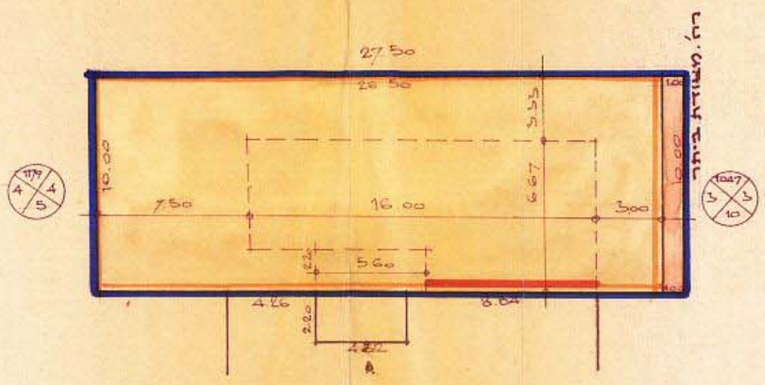

תרשים המגרש

1:250 ק.מ.

מחוז	: תל-אביב
נפה	: תל-אביב - יפו
עיר	: תל-אביב - יפו
היזם	: גאזי יוסף ודליה
בעל הקרקע	: גאזי יוסף ודליה
המתכנן	: מ. יניצקי - מהנדס
גוש	: 6134
חלקה	: 140
שטח	: 275

מקרא

גבול התכנית

אזור מגורים מיוחד

אתור הבנין

קיר משותף

הפקעה - הרחבת דרך



נבדק

תאריך

חתימת היזם :

חתימת בעל הקרקע:

חתימת המתכנן :

תאריך :

גאודע-ניהול ומידע מקרקעין ונכסים בע"מ
אימות אישור
אושרה לתוקף ע"י ועדה
שם
חתימה

משרד הפנים
חוק התכנון והבניה תשכ"ה-1965
מחוז ת"א-מרכז
מרחב תכנון מקומי ת"א-יפו
תכנית שינוי מפת"ר מס' 1482
הוגשה המחוזית בישיבתה ה 295
מיום 6.3.78
החליטה לתת תוקף
ד' ריזניק
יו"ר הוועדה המחוזית לעיל.
יושב ראש הועדה

משרד הפנים
חוק התכנון והבניה תשכ"ה-1965
מחוז ת"א-מרכז
מרחב תכנון מקומי ת"א-יפו
תכנית שינוי מפת"ר מס' 1482
הוגשה המחוזית בישיבתה ה 159
מיום 10.1.72
החליטה להמליץ את
ד' ריזניק
יו"ר הוועדה המחוזית לעיל.
יושב ראש הועדה

הועדה המקומית לתכנון ולבניה תל-אביב יפו
שם התכנית תכנית מפ"ר מס' 1482
הומלצה למתן תוקף ~~ולאחר דיון בהתנגדויות~~
תאריך פרוטוקול החלטה
אושרה למתן תוקף ע"י הועדה המחוזית לתכנון ובניה
תאריך 7.8.72 ישיבה מס' 171
נח' בע. | מהנדס העיר | יו"ר הועדה
תאריך 1.12.77