תשריט מס כ.פ. 6

מרחב תכנון מקומי
תל אביב - יפו

תשריט לתכנית מפורטת מס' 2113
שנוי מס' 1 לשנת 1980 של תכנית מפורטת מס' 1967
ושנוי מס' 1 לשנת 1980 של תכנית מפורטת מס' 465

מחוז	:	תל אביב
נפה	:	תל אביב
עיר	:	תל אביב יפו
גוש	:	6135
חלקות	:	269- 273 , 275 , 276 , 278 וחלקי חלקות: 244, 251, 279.
שטח התכנית	:	כ- 14.70 דונם על פי תכנית 4390 (934) לר על פי מפה טופוגרפית
בעל הקרקע	:	"חלמיש" - שדרי ירושלים 45 תל-יפו. ועירית תל-אביב יפו
היזם	:	הועדה המקומית לתכנון ולבניה תל-אביב - יפו
המתכנן	:	קיי-עדרת אדר' בע"מ שלמה החלוץ 51 תל אביב טל. 239997
תאריכים	:	26.1.77

חלוקות		
בעל הקרקע		
היזם		
המתכנן		

מתאר א-א ק.מ. 1:500

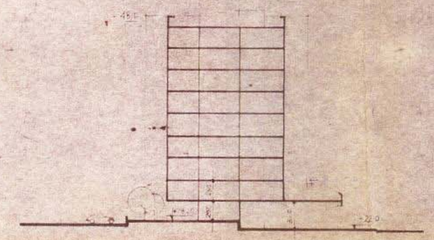

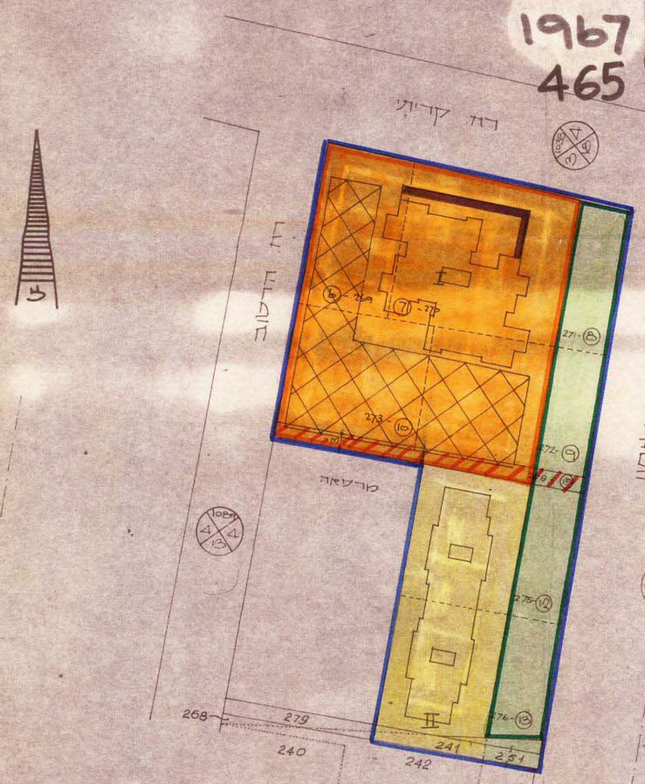

מצב קיים קנ"מ 1:625
לפי תב"ע 1967 ו- 465

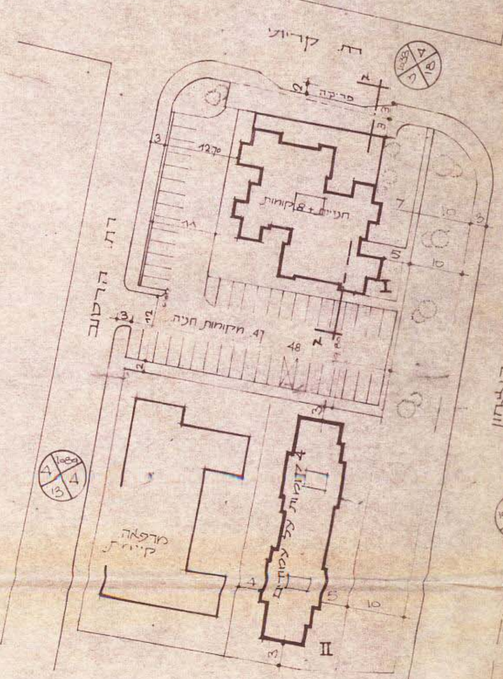

מצב בעוד קנ"מ 1:625

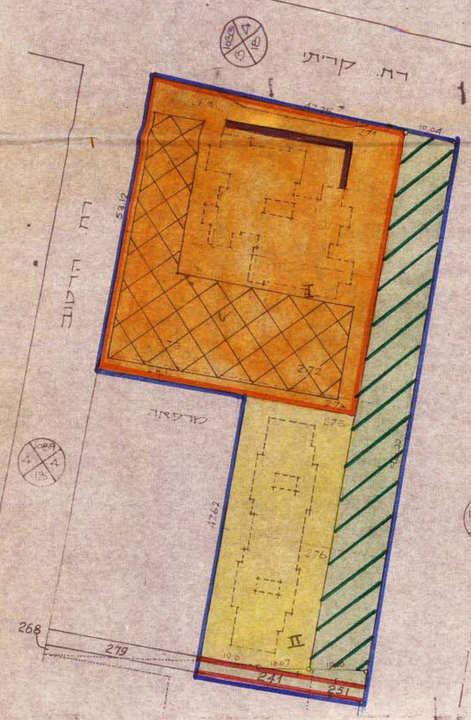

מצב חדש קנ"מ 1:625

תרשים הסביבה 1:10000

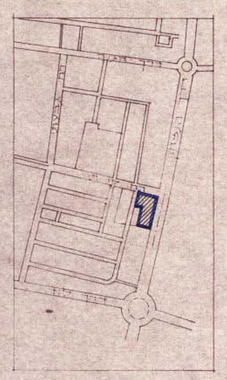

מקרא

- גבול התכנית
- איזור מגורים ג' מאושרת
- חזית חנויות
- חניה פרטית
- שביל הולכי רגל
- שטח פרטי פתוח
- איזור מגורים מיוחד
- דרך לביטול
- שטח לציבורי פתוח מוצע
- קו החלקה
- שטח לציבורי פתוח קיים

חותמות

מדינת ישראל / נשרד הפנים
חוק התכנון והבניה תשכ"ה-1965
מחוז תל-אביב
מרחב תכנון מקומי תל אביב
תוכנית מתאר/מפורטת מס' 2113
הועדה המחוזית בישיבתה מס' 26 ביום 29.10.81 החליטה להפ/תוקן
לתכנית:
מרדכי כהנא
יושב ראש הועדה
סגן מנהל כללי לתכנון
נבדק
תאריך 22.2.82

עירית תל-אביב-יפו
מחלקת ההנדסה / מס' משנה לתכנון ולבנין ערים
שם התכנית: תכנית מפורטת מס' 2113
מס. תרש': 1:625 קנה-מידה:
אישור: מ.ר. תיכנון: ר.ב. ביקורת: ר.ב.
תאריך: 20.12.81 מהנדס העיר: מנהל מח' משנה:

הועדה המקומית לתכנון ובניה תל-אביב-יפו
שם התכנית: תכנית מפורטת מס' 2113
הומלצה לתכנון תוקן לאחר דיון בהתנגדויות:
תאריך 29.10.81 מס' 126
יו"ר הועדה
נהלי עב. מינהל העיר
תאריך 20.12.81

הועדה המקומית לתכנון ובניה תל-אביב-יפו
שם התכנית: תכנית מפורטת מס' 2113
הומלצה להפקדה בישיבתה:
תאריך 20.2.80 פרוטוקול 32 ה' החלטה 1
ר.מ.:
ותוקנה ע"י הועדה המחוזית ואושרה להפקדה
תאריך 13.10.80 בישיבה מס' 348
יו"ר הועדה
תאריך 20.12.81
מס' משנה | תאום תכנון