תוכנית מס' 3560
"מתחם רשף"
תל אביב יפו

מאושרת
סמכות מקומית

תוכנית מתאר מקומית עם הוראות של תוכנית מפורטת

איחוד וחלוקה	סמכות	היתרים / הרשאות
איחוד וחלוקה בהסכמת כל הבעלים בתחום התכנית	ו. מקומית	תכנית שמכוחה ניתן להוציא היתרים או הרשאות

מחוז : תל אביב

מרחב תכנון מקומי: תל אביב יפו

רשות מקומית : תל אביב יפו

שטח התוכנית : 3.464 דונם

קנ"מ 1:500

גושים וחלקות בתוכנית :

מספר גוש	סטטוס גוש	מספרי חלקות בשלמותן	מספרי חלקות בחלקן
6135	מוסדר		4

אישור / חתימת מוסדות תכנון :

הועדה המקומית לתכנון ולבניה תל-אביב-יפו
מרחב תכנון תל-אביב - יפו
חוק התכנון והבנית תשכ"ה - 1965
אישור תכנית מס' 3560
התכנית מאושרת מכח סעיף 109(ג) לחוק
מחל מיום 16/11/07
מנהל התכנון | יו"ר הועדה המקומית | שר הפנים

שלב : מתן תוקף

מהדורה : 1 תאריך : 1/5/07

שמות וחתימות :

מגיש התוכנית	שם : מנהל ההנדסה, אגף תב"ע, עיריית ת"א-יפו		חתימה
	כתובת : שד' בן גוריון 68 תל-אביב	טלפון : אגף תב"ע 03-5217162	
בעלי זכויות בקרקע	שם : עיריית ת"א-יפו		חתימה
	כתובת : רח' אבן גבירול 71 תל-אביב	טלפון : אגף נכסי העירייה 03-5218400	
עורך התוכנית	שם : מנהל ההנדסה, אגף תב"ע, עיריית ת"א-יפו		חתימה
	כתובת : שד' בן גוריון 68 תל-אביב	טלפון : אגף תב"ע 03-5217162	מס' רשיון
מודד התוכנית	שם : שמעון חי - מודד מוסמך		חתימה
	כתובת : רח' שרת 21 רמת גן	טלפון : 0507902848	
			מס' רשיון

מצב קיים קנה מידה 1:500

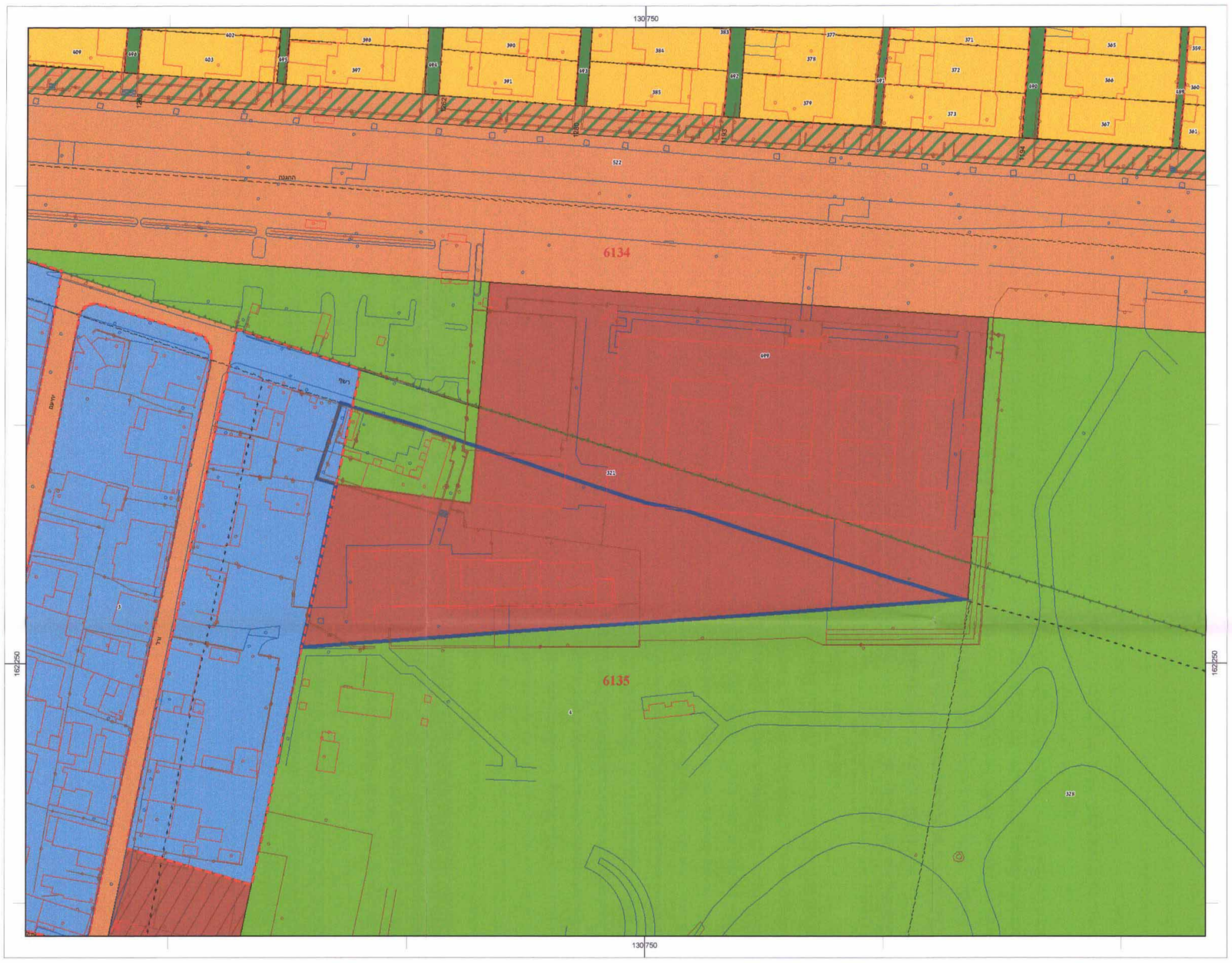

מקרא מצב קיים

- דרך קיימת (*)
- מגורים ב (*)
- שטח ציבורי פתוח (*)
- שביל להולכי רגל (*)
- בנייני ציבור (*)
- מגורים קומה 1 (*)
- בניני ציבור מוצע (*)
- גבול מגרש ראשי (*)
- שצ"פ (*)
- גבול תוכנית
- גושים
- חלקות

(*) לא על פי מבאת

מצב מוצע קנה מידה 1:500

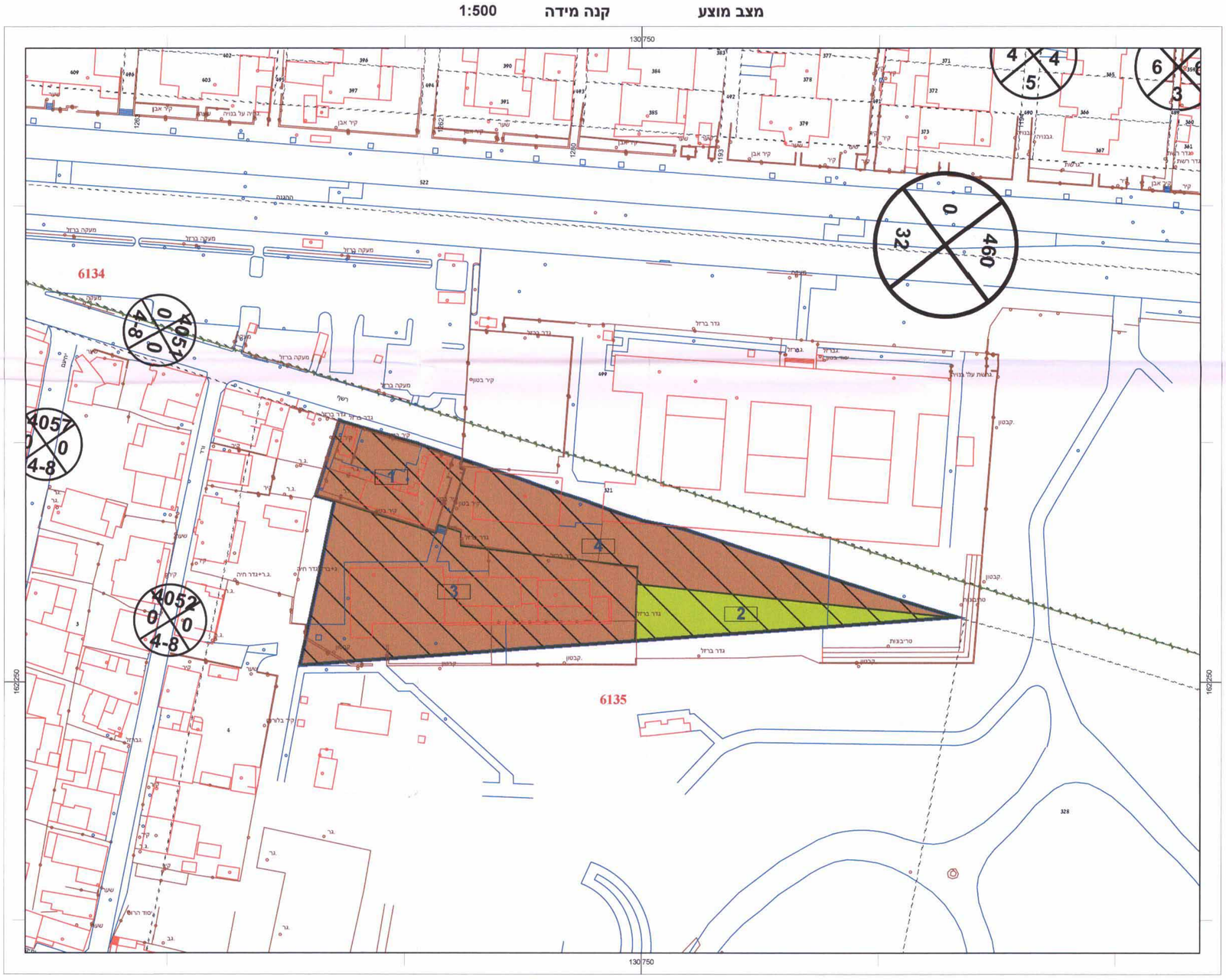

מקרא מצב מוצע

- מבנים ומוסדות ציבור
- שטח ציבורי פתוח
- גבול תא שטח ומספרו
- גבול מגרש מוצע
- שטח לאיחוד וחלוקה חדשה
- רוזטות דרך
- גבול תוכנית
- גושים
- חלקות

טבלת השטחים :

	מצב מאושר		מצב מוצע		
שם ייעוד	שטח ייעוד (מ"ר)	אחוז מהשטח	שם ייעוד	שטח ייעוד (מ"ר)	אחוז מהשטח
מגורים ב (*)	55	1.6	מבנים ומוסדות ציבור	3,074	88.7
שטח ציבורי פתוח (*)	397	11.4	שטח ציבורי פתוח	390	11.3
בנייני ציבור (*)	3,013	87.0			
סך הכל שטח	3,464	100.0	סך הכל שטח	3,464	100.0
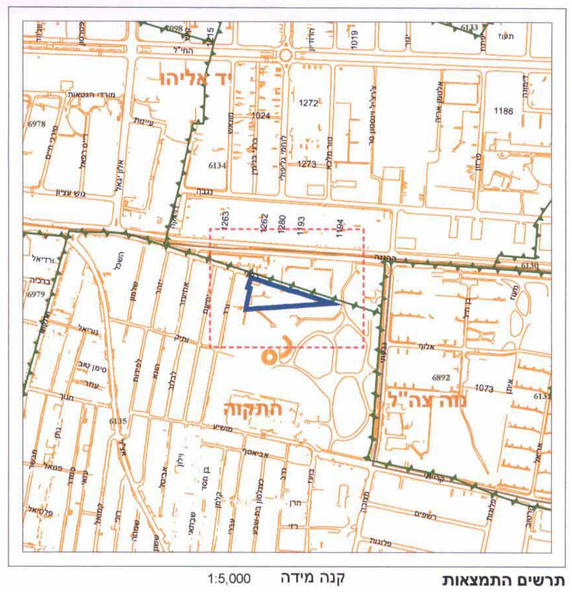
תרשים התמצאות קנה מידה 1:5,000