תסריט מס' ב.ע./68/1390

מרחב תכנון מקומי תל-אביב-יפו
תסריט לתכנית מספר 1236
שנוי מס' 1 לשנת 1968 של תכנית מפורטת מס' 301

מחוז : תל-אביב
נפה : תל-אביב-יפו.
עיר : תל-אביב-יפו.
חלקי גושים 6130, 6135.
היוזם והמתכנן: עת"א הועדה המקומית לתכנון ולבנייה
שטח התכנית: 10 דו'מ

1:1250

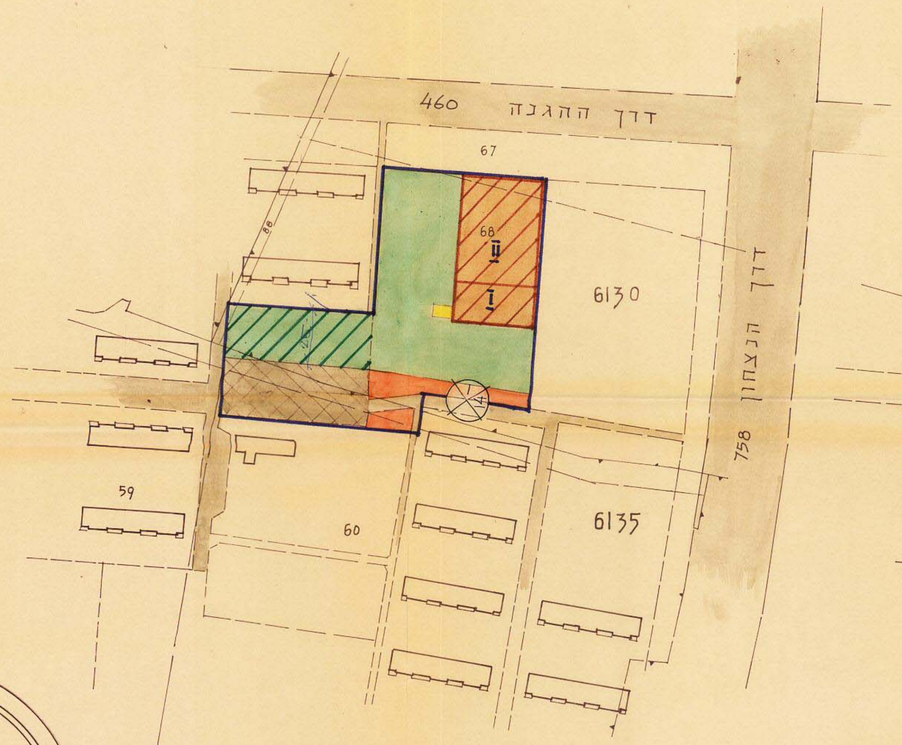

מצב חדש

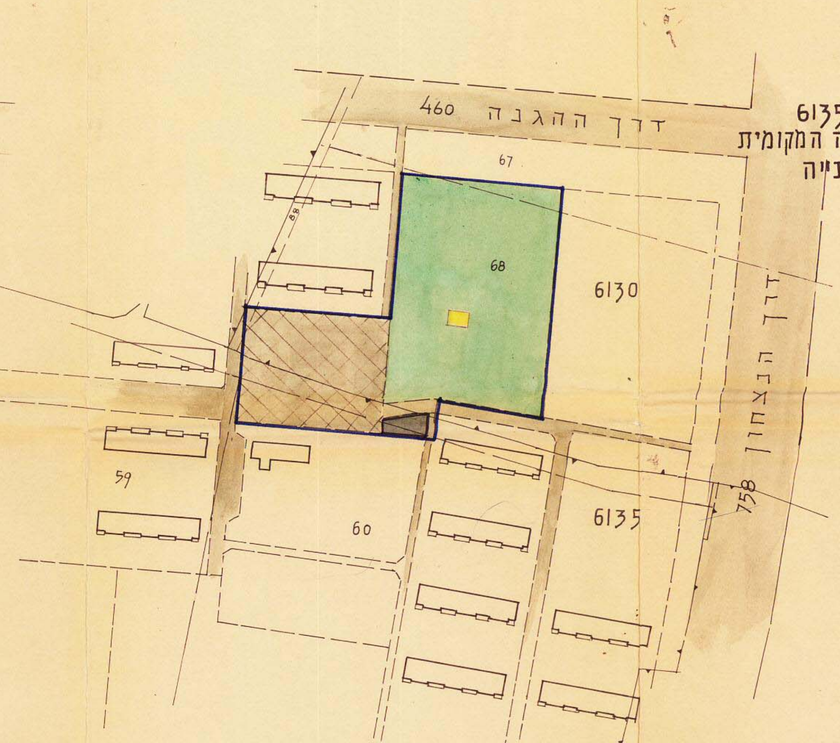

מצב קיים.

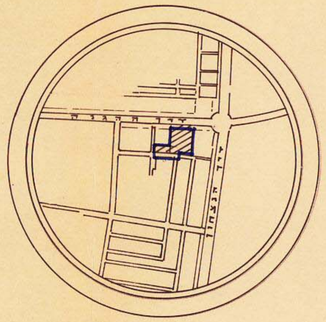

תרשים הסביבה - 10.000

טבלת שטחים

	אזורים	שטח ב מ"ר
1.	שטח צבורי פתוח	5.300
2.	מגרש לבנין צבורי	2.300
3.	דרך וחניה	2.400
		10.000

מקרא

- גבול התכנית
- " הגוש
- " חלקה קיימת
- דרכים קיימות
- " להרחבה
- בנינים להריסה
- שטח צבורי פתוח קיים
- שטח צבורי פתוח מוצע
- שטח מוצע לבניני צבור
- חנייה
- אזור מסחרי

משרד הפנים
חוק התכנון והבניה תשכ"ה-1965
מרחב תכנון מקומי תל-אביב-יפו
תכנית מפורטת מס 1236
הועדה המחוזית בישיבתה ה 51
מיום 24.6.68 החליטה להפקיד את התכנית בהתאם לעל
ד. רזניק
יו"ר הועדה המחוזית
28.5.70 נדפס אייר תשל"

משרד הפנים
חוק התכנון והבניה תשכ"ה-1965
מרחב תכנון מקומי תל-אביב-יפו
הועדה המקומית לתכנון ולבניה תל-אביב-יפו
שם התכנית: תכנית מס' 1236
הוגשה לאישור הועדה המחוזית בישיבתה מס 63 מיום 25.11.68
12.2.70

עיריית תל-אביב-יפו
מחלקת ההנדסה / מס' משנה לתכנון ולבנין עיר
שם התכנית: תכנית מס' 1236
מס. סדורי: 1390 קנ"מ: 1:1250
חישב: מרד: תיכנן: שרטט: ביקר:
מנהל מח' משנה: מהנדס העיר: תאריך: 8.1.68