מרחב תכנון מקומי תל אביב-יפו

תשריט מצורף לתכנית מפורטת מס' 2015

מחוז תל-אביב

נפה

עיר תל אביב-יפו

גוש 6135

חלקה חלקה (69,51,50)

שטח התכנית 6.432 דונם

היוזם הועדה המקומית לתכנון ובנין עיר ת"א יפו

בעל הקרקע עירית תל אביב-יפו

המגיש משרד הבנוי והשכון

עורך התכנית משרד הבנוי והשכון/מחוז מרכז

קנה מידה 1:625

תאריך 13.1 .81

מ ק ר א

גבול התכנית

אזור מגורים

שטח ציבורי פתוח+מדרחוב

דרך או הרחבה מוצעת

חניה

דרך קיימת

גבול חלקה קיימת

גבול חלקה מוצעת

בנין קיים

בנין מוצע

בנין קיים להריסה

מספר חלקה קיימת (70)

מספר חלקה חדשה 3

חתימת בעל הקרקע

חתימת היוזם

חתימת עורך התכנית

אשורים וחתימות

מדינת ישראל / משרד הבינוי והשיכון
מרחב תכנון מקומי תל אביב יפו
תכנית מס' 2015
352
19.1.81
6235

נאמדע-ניהול ומידע מקרקעין ונכסים בע"מ
אימות אישור
אושרה לנוקף ע"י ועדה
שם
חתימה

תכנית מס' 2015
56 247
31.12.80

אושרה לפקדון תוקף ע"י הועדה השאיית לתכנון ולבניה
352
19.1.81
11.12.83

חלמיש - חב' למשלחת עירונית
לשיקום והיורב בתל אביב-יפו בע"מ
ציר ירושלים 45 תל אביב 83525256

משרד הבינוי והשיכון
מחוז המרכז
רח' החשמונאים 13
תל-אביב

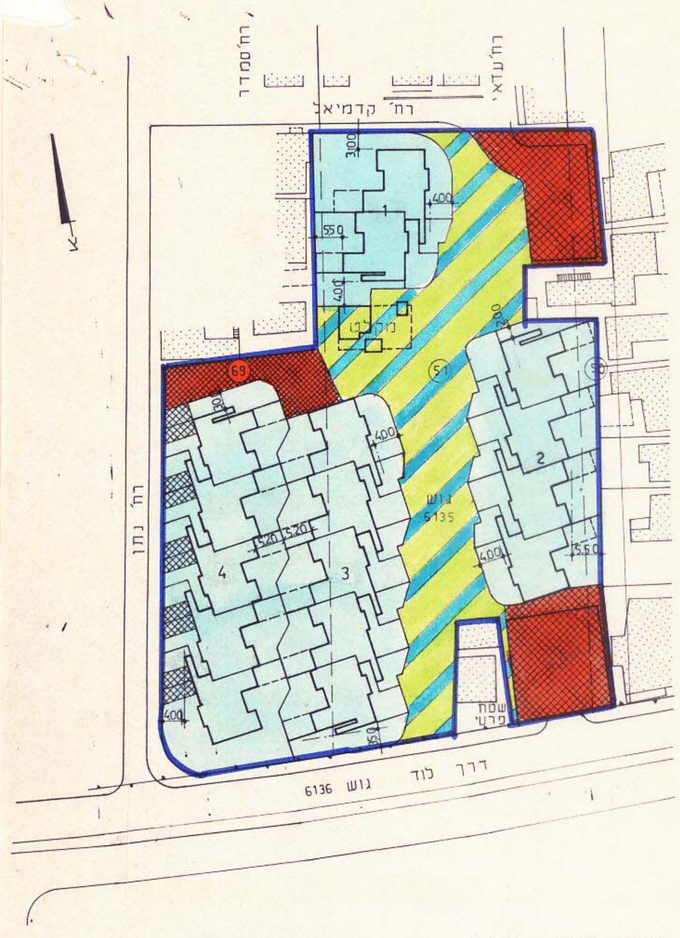

מצב מוצע 1:625

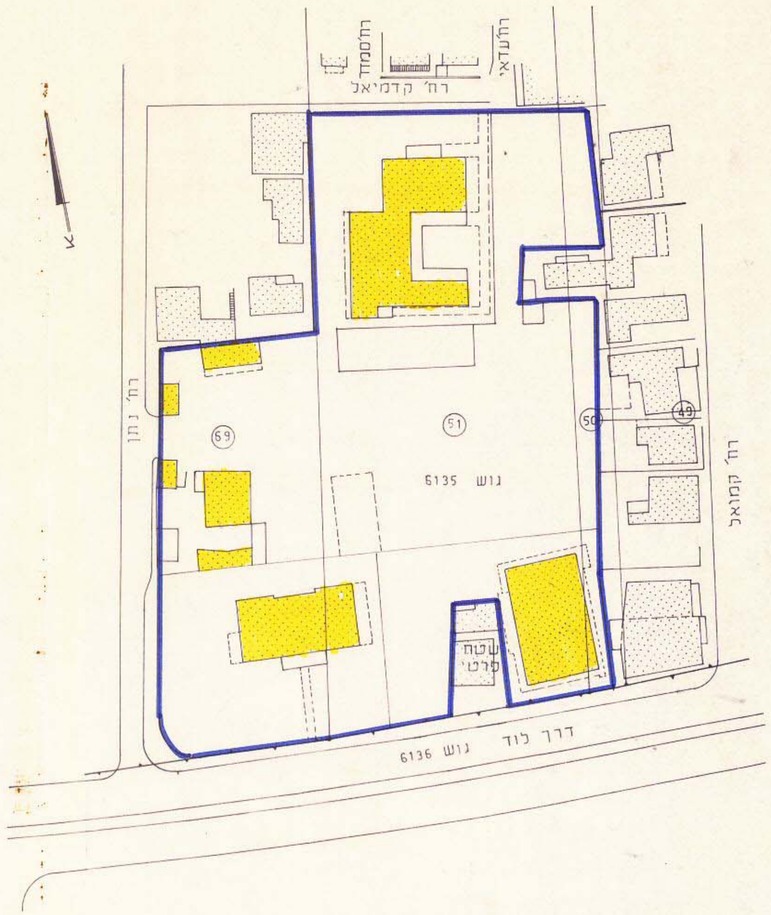

מצב קיים 1:625

טבלת שטחים - והקצאות

מס' חלקה חדשה	מגורים במ"ר	שצ.פ	דרכים וחניות	מס' קומות	מס' יחידות	הערות
1	640.00			2	4	
2	1010.00			2	8	
3	1243.00			2	10	
4	1311.00			2	10	
		1368.00				
			860.00			
סה"כ	4204.00	1368.00	860.00	2	32	
סה"כ כללי 6432.00 מ"ר						

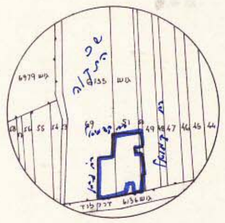

תרשים סביבה 1:6250

19.1.81