מרחב תכנון מקומי תל אביב יפו

תשריט לתכנית מפורטת מס 3139

"אילון על הפארק" - תכנית בסמכות הועדה המקומית

שינוי מס 1 לשנת 2000 של תכנית מתאר מס 2620 ב.מ 55
תכנית איחוד וחלוקה בהסכמה

מחוז	- תל אביב
נפה	- תל אביב-יפו
עיר	- תל אביב-יפו
גוש	- 6136
חלקות	- 66,49,44
חלקי חלקות	- 69,72,71,70,52,4
גוש	- 6137
חלקי חלקות	- 8
מיגרשים	- 605,604,603,402,401
שטח התכנית	- כ-28 דונם
היזם	- חברת 'פרידמן-חכשורי' חברת 'אביוד'
בעל הקרקע	- מנהל מקרקעי ישראל עיריית ת"א יפו
המתכנן	- אדריכל דורון צפריר

התשריט הוכן על בסיס מיפוי פוטוגרמטרי בק.מ. 1:500 ערוך ע"י מודד מוסמך

חתימת המתכנן
אדריכל דורון צפריר
רח' אדם הכהן 16 ת"א 64585
טל. 03-5230425 פקס. 03-5239997

חתימת היזם (שאינו הועדה)
אביוד חברה לבנין ועבודה
פרידמן חכשורי חברה להנדסה ובנין בע"מ

חתימת בעל הקרקע

חתימת הועדה המקומית
ועדה מקומית תל-אביב-יפו
אישור תכנית מס' 3139
הוועדה המקומית החליטה לאשר את התכנית
הנ"ל בישיבה מס' 2002-1 מיום 23/01/02
מהנדס העיר
תל-אביב

הרי גרינברג מדידות בע"מ
הרי גרינברג-מודד מוסמך
רשיון מס' 397

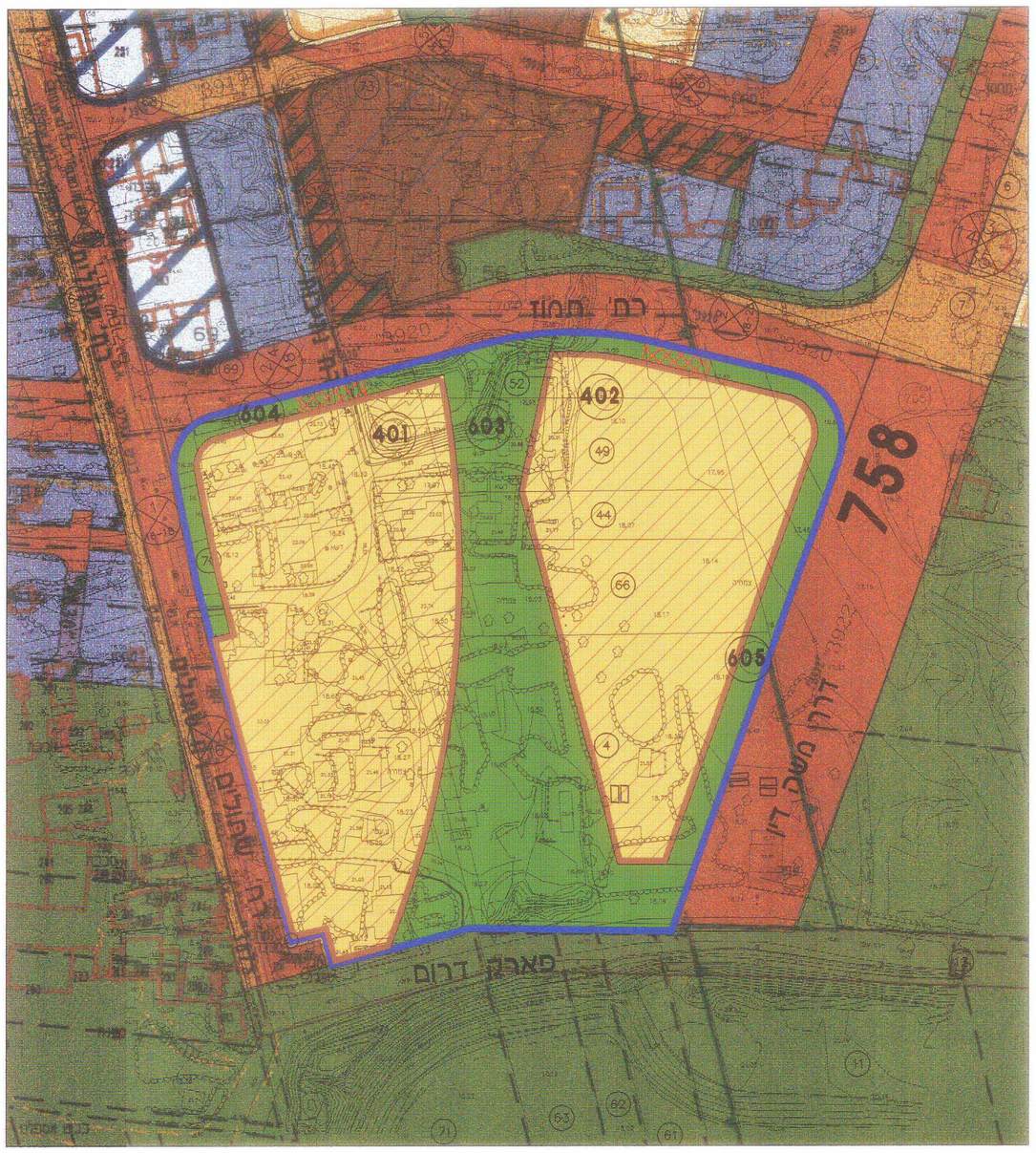

מצב מוצע 1:1250

הרי גרינברג מדידות בע"מ
הרי גרינברג-מודד מוסמך
רשיון מס' 397
2.11.2001

הרי גרינברג
מדידות (1992) בע"מ
תל-חי 4, חולון
טל. 5055187, פקס. 03-5012283

תרשים סביבה 1:50,000

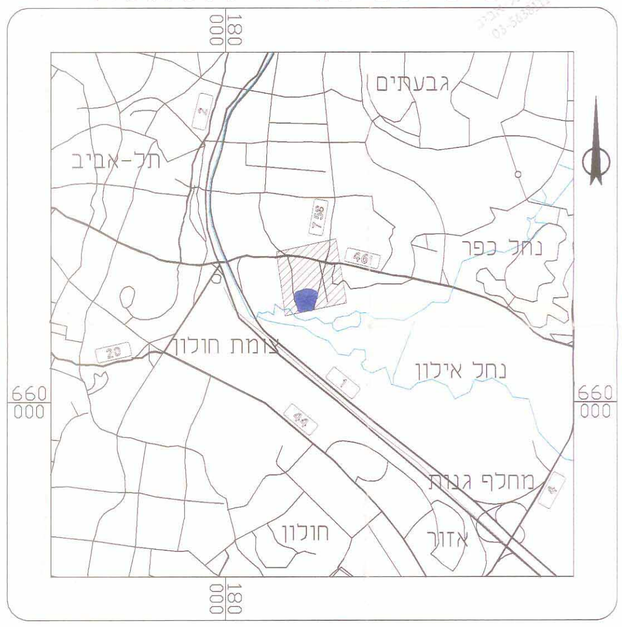

1:5000

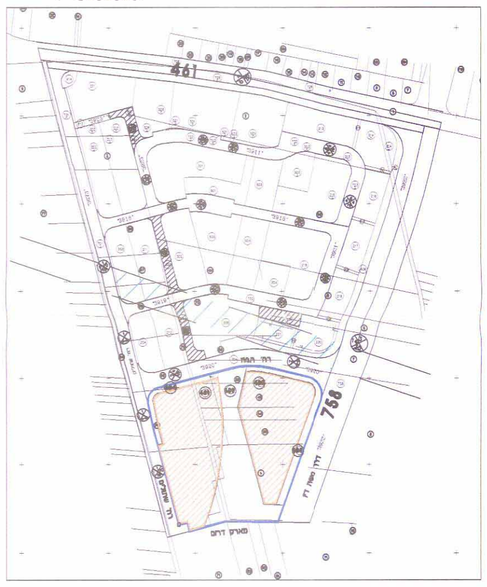

מקרא

- גבול תכנית
- זיקת הנאה למעבר כלי רכב
- ש.צ.פ
- אזור מגורים מיוחד א
- איזור מגורים מיוחד
- איזור מגורים ב
- איזור מגורים ב1
- שטח למבני ציבור מוצע
- דרך קיימת ומאושרת
- דרך מוצעת
- דרך משולבת
- 402 מספר מגרש
- 66 מספר חלקה

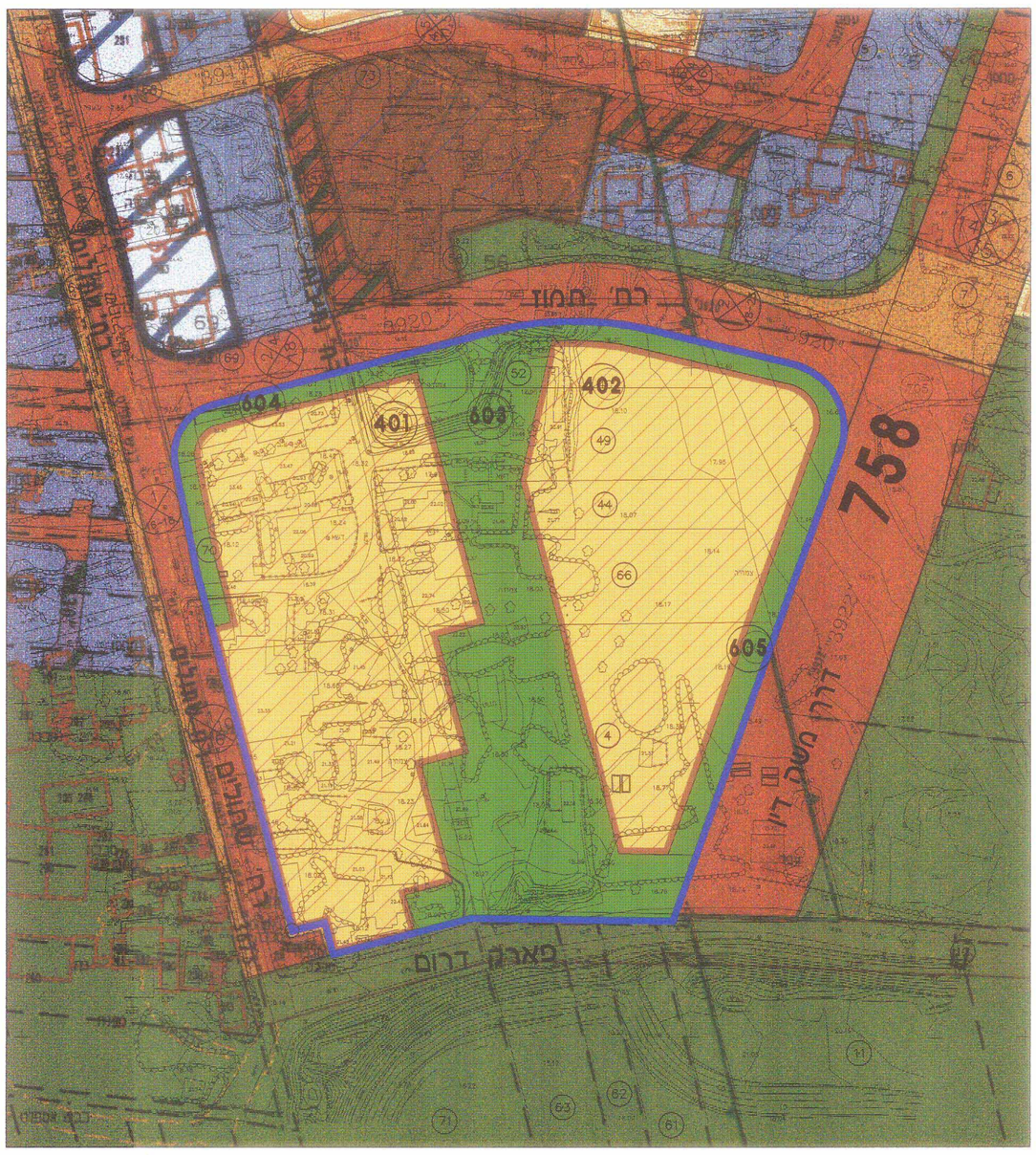

מצב קיים 1:1250

הרי גרינברג מדידות בע"מ
הרי גרינברג-מודד מוסמך
רשיון מס' 397
2.11.2001

הרי גרינברג
מדידות (1992) בע"מ
תל-חי 4, חולון
טל. 5055187, פקס. 03-5012283

טבלת שטחים

מס מיגרש	שטח קיים	שטח מוצע	יעוד
401	10.209	10.209	אזור מגורים מיוחד א
402	8.534	8.534	אזור מגורים מיוחד א
603	6.845	6.845	ש.צ.פ
604	0.784	0.784	ש.צ.פ
605	1.655	1.655	ש.צ.פ
	28.027	28.027	

tasrit