חוק התכנון והבניה, התשכ"ה - 1965
תכנית מתאר מקומית

מס' 507-0884080

תא/מק/ 4899 - רה פרצלציה בגוש 7069 שכונת התקווה

תשריט מצב מוצע	גיליון 1 מתוך 1
מחוז	תל-אביב
מרחב תכנון מקומי	תל אביב-יפו
רשות מקומית	תל אביב-יפו
ישוב	תל אביב-יפו
תכנית בסמכות	מקומית
איחוד וחלוקה	איחוד ו/או חלוקה בהסכמת כל הבעלים בכל תחום התכנית/בחלק מתחום התכנית
היתרים או הרשאות	תכנית שמכוחה ניתן להוציא היתרים או הרשאות
מונה תדפיס התשריט	31
מועד הפקה	21/12/2023 15:46
שטח התכנית	8.19 דונם קנה מידה 1:500

אישורים בתכנית מס' 507-0884080

שמות*

מגיש התכנית	ועדה מקומית תאריך: ועדה מקומית לתכנון ובניה תל אביב
עורך ראשי	א.סנדלר ע.בורנשטיין תאריך:
יזם	ועדה מקומית תאריך: ועדה מקומית לתכנון ובניה תל אביב

טבלת גושים וחלקות*

מספר גוש	חלק/ כל הגוש	מספרי חלקות בשלמות	מספרי חלקות בחלקיותן
7069	חלק	81, 139	

* הרשימה המלאה מפורטת בהוראות התכנית / בהודעה שפורסמה בעיתונות וברשומות

הריני מצהיר בזאת כי המפה הטופוגרפית/המצבית המהווה רקע לתכנית זו, נערכה על ידי ביום 17-12-2019 והיא הוכנה לפי הוראות נוהל מבא"ת ובהתאם להוראות החוק ולתקנות המודדים שבתוקף.
דיוק הקו הכחול והקדסטר: מדידה אנליטית מלאה ברמת תצ"ר

רם בן חיים	723		
שם המודד	מספר רשיון	חתימה	תאריך

מקרא

- גבול תכנית
- גוש 1234 גבול גוש מוסדר
- 1234 חלקה מוסדרת
- גבול חלקה מוסדרת
- 1 גבול חלקה
- 1 2 3 4 רחוק דרך / מאפר בחוץ / מאפר בפנים / רחוב בחוץ
- מגורים ב
- מבנים ומוסדות ציבור
- שטח ציבורי פתוח
- דרך מאושרת
- דרך מוצעת
- דרך משולבת
- דרך/מסילה לביטול
- דיקת הצאה למעבר רכב
- דיקת הצאה
- שטח להשלמה
- שטח לאיחוד וחלוקה חדשה
- קו בנין ע"י
- מידות

תרשים התמצאות - קנ"מ 1:12000

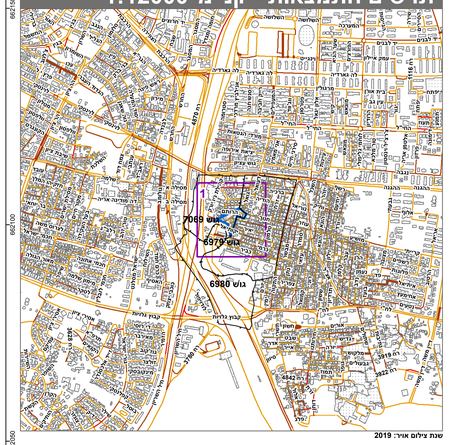

שנת צילום אויר: 2019
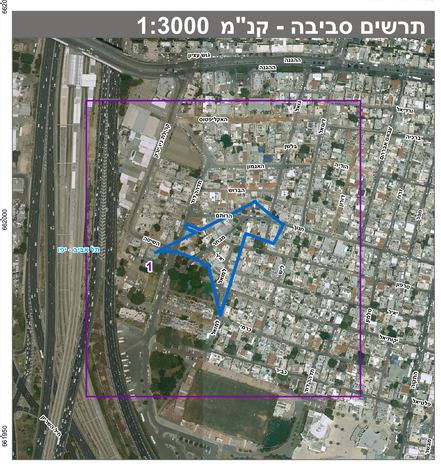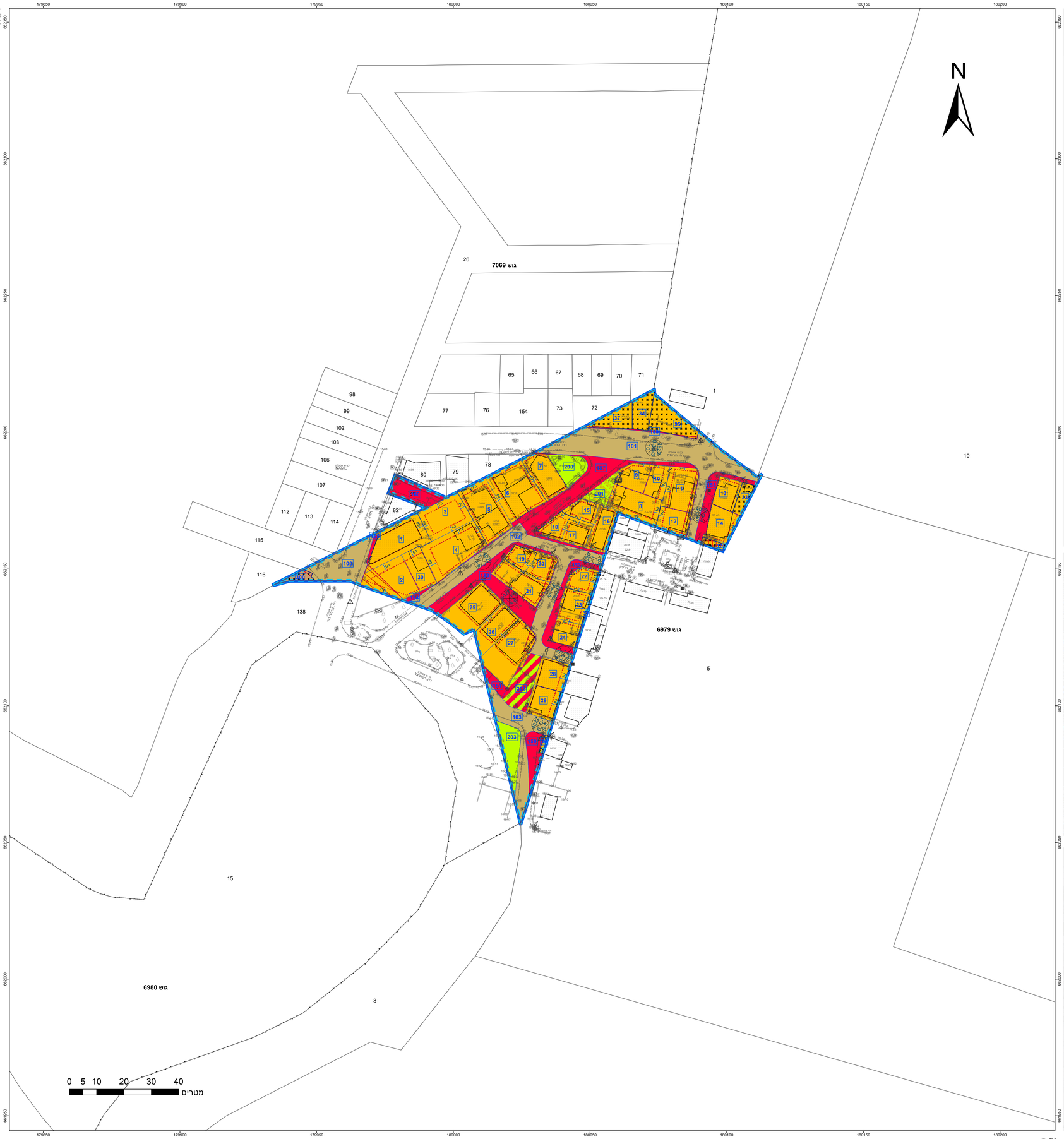
תרשים סביבה - קנ"מ 1:3000