אסיל מס. 101
1660 965-1
2

מרחב תכנון מקומי תל אביב-יפו

תסריט לתכנית מס. 1660

שינוי מס. 1 לשנת 1972 של תכנית מס. - 1049

קנ"מ 1=500

מחוז	:	תל אביב
נפה	:	תל אביב-יפו
עיר	:	תל אביב-יפו
גוש	:	6134
חלקות	:	316, 315, 314, 313, 475, 474, 445
כתל הקיקה	:	צירות תל אביב-יפו
בולם	:	צירות תל אביב-יפו
בתכנון	:	ב. מזרחי - ש. ברון - מ. רוזן
שטח התכנית	:	3732 מ"ר

מקרא :

- גבול התכנית
- ציר הרחבה
- גבול חלקי רחל
- גבולות אזורים ב
- מספר הבנין
- קו בנין
- רוחב הכביש
- חניה פרטית
- מספר חלקה קיימת 313
- מספר הגוש האזור A
- גבול הגוש האזור
- מס הבנין
- בנין אזור מעל בור
- גובה הבנין

תכנית 1=500

שטח המגרש לבנין - 3430 מ"ר

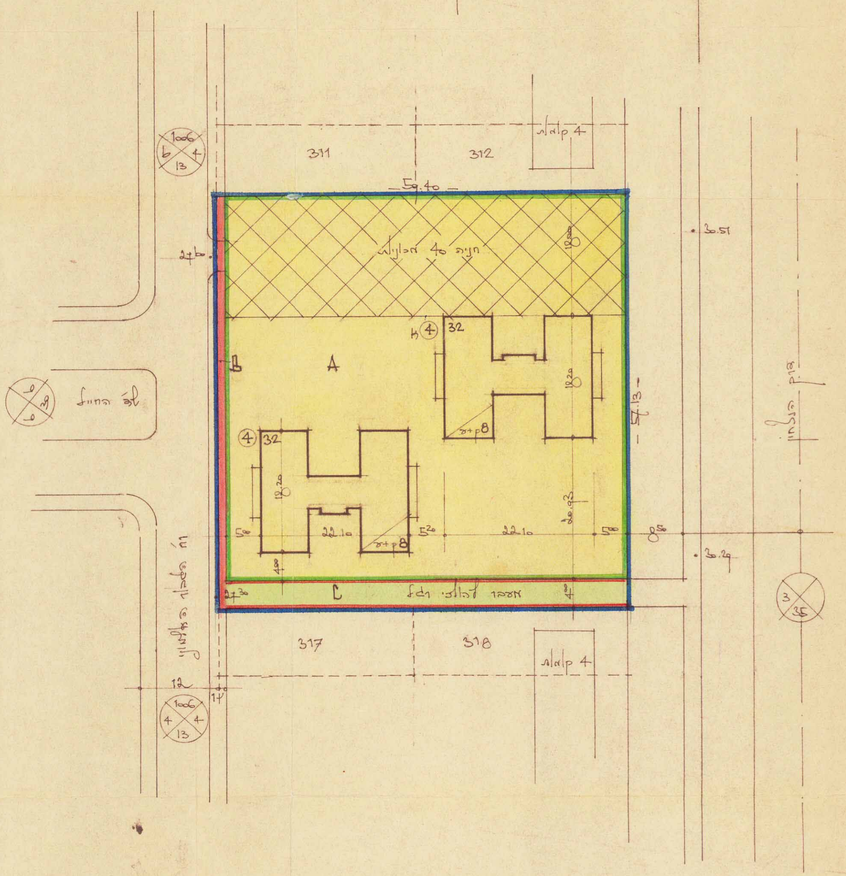

חלקות קיימות - בגוש 6134

מספר החלקה	שטח החלקה
311	313
312	314
311	315
313	316
2121	445
182	474
181	475

סה"כ 3732 מ"ר

רשימת השטחים

A - שטח מגרש לבנין 3430
B - שטח לרחבת הכביש 61
C - שטח גבול לגוש רחל 241

סה"כ 3732 מ"ר

רשימת שטחי הבנים

מספר אזור	שטח המגרש	אזור הבנין	אזור הקומות	אזור מרובע בור	שטח בנין נטו = סה"כ
A	3430	4	8	32	2280 = 285 × 8
		4	8	32	2280 = 285 × 8

סה"כ 4560 מ"ר 64 מרובע

אחוזי בנייה יחיד 122.4% מעשה הקרקע

מרשם סביבה 1=10.000 קנ"מ

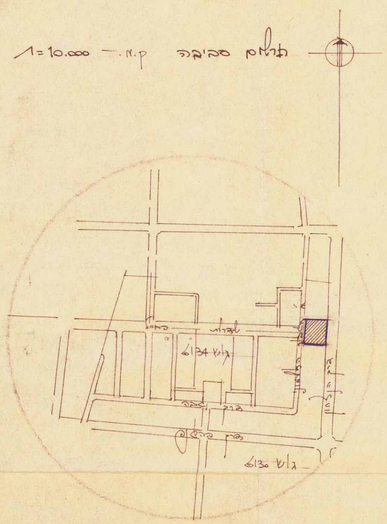

מצב קיים - לפי תב"ע 1049

קנ"מ 1=1250

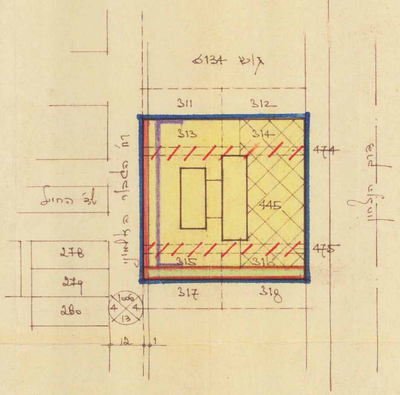

משרד הפנים
חוק התכנון והבניה תשכ"ה-1965
מחוז תל אביב
מרחב תכנון מקומי תל אביב
תכנית מס' 1660
הועדה המחוזית בישיבתה מ' 83
מיום 22.8.83 החליטה להפקיד את התכנית
ר. ו. ניש
יושב ראש הועדה
פקד מנהל

חוק התכנון והבניה תשכ"ה-1965
מחוז תל אביב
מרחב תכנון מקומי תל אביב
תכנית מס' 1660
הועדה המחוזית בישיבתה מ' 27.6.74 החליטה לתת תוקף לתכנית המפורטת לעיל.
ד. ר. ניש
פקד מנהל כללי להתכנון

הועדה המקומית לתכנון ולבניה תל אביב - יפו
שם התכנית תכנית מס' 1660
הוגשה לפקח ביום 14.8.89 פרוטוקול 2280 מתאריך 12.12.73
אושרה לפקח ביום 27.6.74
הערות
6.11.74

חתימת המתכנן :

חתימות בעלי הקרקע :

27.10.74